ОБЩЕСТВО С ОГРАНИЧЕННОЙ ОТВЕТСТВЕННОСТЬЮ «Инженерные изыскания»

Некомерческое партнерство «Объединение инженеров-изыскателей в строительстве»
СРО-И-027-03032010
Свидетельство № 0096.00-2011-5050093095-И-027 от 15 декабря 2011 г.

СОГЛАСОВАНО
Генеральный директор
ООО «Высота»

_____ И.Н. Гарин
06 мая 2025 г.
М.П.

УТВЕРЖДАЮ
Генеральный директор
ООО «Инженерные изыскания»

_____ А.В. Шульго
06 мая 2025 г.
М.П.

СОГЛАСОВАНО
Первый зам. генерального директора
ГКУ МО «ДЗКС»

_____ А.А. Барсков
06 мая 2025 г.
М.П.

МБОУ СОШ на 1100 мест : Московская область, г. о. Королев, ЖК "Золотые ворота"

ПРОГРАММА
ИНЖЕНЕРНО-ГЕОДЕЗИЧЕСКИХ ИЗЫСКАНИЙ

819-ИГДИ-П

Начальник
Инженерно-геодезического отдела М.В. Семенов

Щелково, 2025

Взам. инв. №	
Подп. и дата	
Инв. № подл.	

Обозначение	Наименование	Примечание
819-ИГДИ-П-С	Содержание	с. 2
819-ИГДИ-П-Т	Текстовая часть	с. 3
	Графическая часть	
819-ИГДИ-П-Г.1	Картограмма топографо-геодезической изученности	с. 25

Согласовано

Взам. инв. №

Подп. и дата

Инв. № подл.

Изм.	Кол.уч	Лист	№док.	Подп.	Дата
Разработал		Ковов В.Н.			06.05.25
Проверил		Бешар Л.В.			06.05.25

819-ИГДИ-П-С

Содержание

Стадия	Лист	Листов
И	1	1

ООО «Инженерные изыскания»
г. Щелково

Оглавление

1 Общие сведения 2
2 Изученность территории 5
3 Краткая характеристика района работ 5
4 Состав и виды работ, организация их выполнения 7
5 Контроль качества и приемка работ 13
6 Используемые документы и материалы 14
7 Представляемые отчетные материалы 15
Приложение А Выписка из реестра членов СРО 16
Приложение Б Техническое задание 18
Приложение В Выписка из Административного регламента 22

1 Общие сведения

1.1. Наименование объекта: «МБОУ СОШ на 1100 мест: Московская область, г. о. Королев, ЖК "Золотые ворота".

1.2. Заказчик: ООО «Высота». Генеральный директор Гарин Иван Николаевич. Юридический адрес: 143968, Московская область, г.о. Реутов, г. Реутов, проезд Северный, д. 7. ИНН 5012034645; КПП 504101001. Телефон 8-977-457-70-97, E-mail: smrzakaz@gmail.com

1.3. Исполнитель работ – ООО «Инженерные изыскания». Генеральный директор Шульго Анатолий Владимирович. Юридический адрес: 141107, Московская обл., г. Щелково, ул. Браварская, д. 2В, строение 1, помещение 25. тел.: 8 (496) 563-60-20, E-mail: 0064900@mail.ru, ИНН 5050093095, КПП 505001001.

1.4. Работы выполняются согласно договора № ВЫС-ИИ-СОШ1100К от 22.04.2025 на выполнение инженерных изысканий и требований технического задания, приложение 4 к договору.

1.5. Местоположение объекта: Московская область, г. Королев, в 33 метрах по направлению на юг от д. 12/14 по ул. Гагарина.

1.6. Земельный участок 50:45:0040322:1152, Категория земель: Земли населённых пунктов, Разрешенное использование: для строительства общеобразовательной школы на 1100 мест.

1.7. Ориентировочная площадь участка топографической съемки – 4.98 га. Ориентировочная площадь подеревной съемки – 2.5 га.

1.8. Вид градостроительной деятельности – Новое строительство.

1.9. Вид инженерных изысканий (см. п.5.3 СП 47.13330.2016) - Инженерно-геодезические изыскания для архитектурно-строительного проектирования при подготовке проектной документации объектов капитального строительства.

1.10. Этапы инженерно-геодезические изысканий: выполнить первый этап п. (5.3.1 СП 47.13330.2016).

1.11. Цели и задачи инженерно-геодезических изысканий: получение исходных топографо-геодезических данных: инженерно-топографических планов в графическом и/или цифровом видах представления информации; сведений о координатах и отметках точек местности; количественных характеристик развития опасных природных и техногенных процессов; иных материалов и данных, необходимых для разработки схемы планировочной организации земельного участка расположения проектируемого объекта капитального строительства и обеспечения выполнения других видов инженерных изысканий.

1.12. Материалы, предоставляемые Заказчиком: схема границ топографической съемки.

1.13. Принадлежность к объектам транспортной инфраструктуры и к другим объектам, функционально-технологические особенности которых влияют на их безопасность: не принадлежит.

1.14. Возможность опасных природных процессов и явлений и техногенных воздействий на территории, на которой будут осуществляться строительство, реконструкция и эксплуатация здания или сооружения: не прогнозируется.

1.15. Принадлежность к опасным производственным объектам: не принадлежит.

1.16. Класс функциональной пожарной опасности: Ф4.1 (Федеральный закон от 22 июля 2008 г. N 123-ФЗ «Технический регламент о требованиях пожарной безопасности»).

1.17. Класс конструктивной пожарной опасности: С0, Степень огнестойкости II.

1.18. Класс возможного пожара на объекте: определить по результатам инженерных изысканий (комплексноо инженерно-технического обследования состояния объекта), в соответствии с требованиями Федерального закона от 22.07.2028 № 123-ФЗ «Технический регламент о требованиях пожарной безопасности».

1.19. Уровень ответственности объекта: нормальный.

1.20. Характеристики проектируемых задний и сооружений: Общая площадь: 3904.1 м^2; площадь ЗУ 2262 м^2; площадь застройки 1646.1 м^2; строительный объем 19164 м^3.

1.21. Период выполнения полевых работ: благоприятный – май.

1.22. Подготовка и утверждение заданий на выполнение работ, отбор участников, координация их действий, представление, согласование и приемка результатов работ осуществляются специалистом по организации инженерных изысканий, зарегистрированным в национальном реестре специалистов.

1.23. Обзорная схема размещения объекта представлена на рис. 1. На схеме синей линией обозначены границы топографической съемки, а красной границы подеревной съемки.

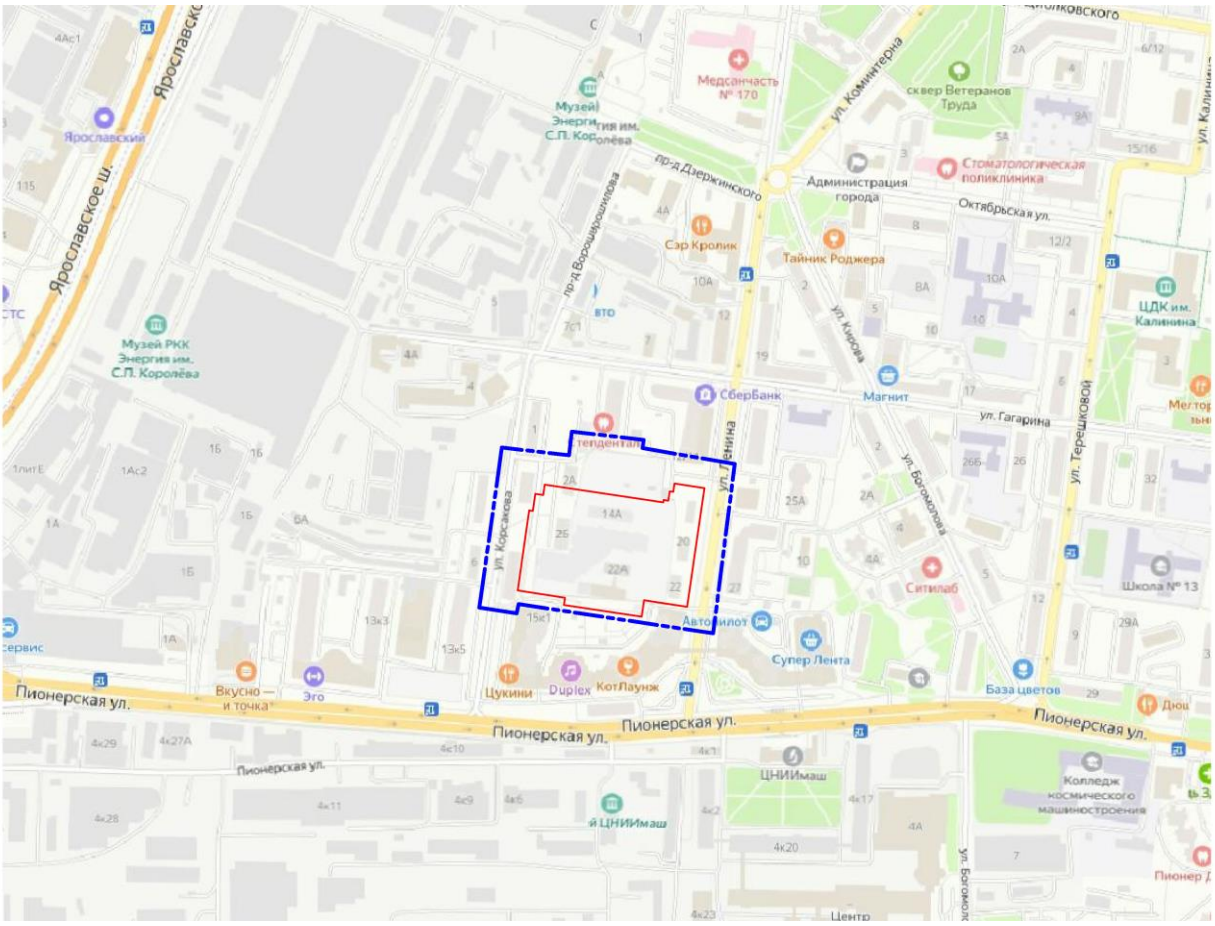

Рисунок 1 - Обзорная схема размещения объекта

Взам. инв. №	
Подп. и дата	
Инв. № подл.	

Изм.	Кол.у	Лист	№док	Подп.	Дата	819-ИГДИ-П-Т	Лист 4

Формат

2 Изученность территории

При получении технического задания Заказчиком был предоставлен ситуационный план с границами участка съемки. Для ориентирования на местности использовались электронные карты Яндекс и Гугл. Для определения характеристик кадастровых участков использовались данные Публичной кадастровой карты Росреесто. Для поиска ближайших пунктов государственной геодезической сети, и референцных станций сети специального назначения использовался ресурс Федерального портала пространственных данных. По данным сайта ГБУ "БТИ Московской области" рабочие зоны референцных станций сети «СТП МОБТИ» покрывают всю территорию Московской области. Картограмма топографо-геодезической изученности представлена в графической части программы.

3 Краткая характеристика района работ

Объект расположен в городском округе Королев. Участок съемки представляет собой застроенную территорию 2 категории сложности.

Королёв (основан 26 декабря 1938 года; до 8 июля 1996 года — Калининград) — город в Московской области России, наукоград (с 12 апреля 2001 года). Население — 224 348 человек (2024). Самый большой по населению наукоград. Королёв часто неофициально называют космической столицей России. Город областного подчинения, образует одноимённый городской округ. В мае 2014 года в состав города был включён упразднённый город Юбилейный.

География. Город расположен к северо-востоку от Москвы, в 23 км от центра и в 6—7 км от МКАД по Ярославскому шоссе. Ярославское шоссе является западной границей Королёва (исключая Залинейный район). С юга к городу примыкает Национальный парк «Лосиный Остров», а с севера и востока — дачные посёлки. В городе протекает река Клязьма, а также много мелких рек (в части Лосиного Острова). Лесные массивы в черте города занимают территорию 3800 га. Также в черте города находится часть урочища «Яузский водоболотный комплекс».

Площадь, занимаемая гордским округом, 55,47 км. При этом площадь территории собственно города в его традиционных границах ранее составляла 38,82 км². Городская черта и границы городского округа в значительной части не совпадают, Генеральным планом городского округа установлена городская черта города Королёва, которая исключает те земли городского округа, которые заняты лесами, болотами и сельскохозяйственными угодьями; площадь собственно города Королёва (в пределах его городской черты, включающей все прежние населённые пункты, которые были объединены с городом) составляет 35,5877 км².

Городской округ Королёва граничит с городскими округами Ивантеевка (на северо-

востоке), Щёлково (на востоке), Балашиха (на юге), Мытищи (на западе) и Пушкинским городским округом (на севере)

Климат в городском округе Королёв относится к умеренно-континентальному, находится под влиянием воздушных масс, идущих с Атлантики и Арктики. Господствующие ветры: северо-западного и юго-западного направлений. Это характерно для климата Подмосковья. Среднегодовая температура +4,8 °С; абсолютный минимум −43 °С, абсолютный максимум +38 °С. Средняя расчётная температура наиболее холодного месяца −8,8 °С. Средняя максимальная температура наиболее жаркого месяца +23,8 °С. Средняя многолетняя температура верхних слоёв почвы (на глубине 0,2 м) достигает +18,9 °С в июле, и −6,2 °С — в январе-феврале.

Появление снежного покрова наблюдается (в среднем) с 3 ноября, образование устойчивого покрова — с 26 ноября. Разрушение покрова начинается в среднем 6 апреля, сход снега происходит 11 апреля. Сохраняется снежный покров примерно 140 дней. Его высота в течение зимнего периода возрастает от 2—5 см в ноябре до 30—40 см во второй-третьей декаде февраля. Число дней с осадками составляет 182—183. Среднее число дней с различными видами оледенений за год — 24.

Среднемесячная скорость ветра колеблется от 1,7 до 4,0 м/с, в среднем за год в районе ВДНХ составляет 2,2 м/сек, на территории Лосиного острова — 3,5 м/с. В зимний период наблюдаются наибольшие скорости ветра. Преобладающими в годовом ходе являются ветры южных, юго-западных и западных румбов, в период с июня по октябрь явно преобладают ветры западного направления.

Природная зона лесная. Подзона широколиственных и хвойных лесов с элементами степной флоры.

Транспортная сеть имеет достаточное развитие, в связи с расположением района вблизи г. Москвы. Участок съемки представляет собой застроенную территорию, рельеф ровный, без уклонов, к месту проведения работ имеется подъезд. В границах изысканий объектов гидрографии нет.

4 Состав и виды работ, организация их выполнения

Исходными пунктами для создания исходной геодезической сети служат ближайшие пункты сети постоянно действующих базовых станций (например, сети EFT-CORS), координаты и высоты которых определены от пунктов ГГС и включены в федеральный фонд пространственных данных (ФФПД). Сеть создается методом GPS-ГЛОНАСС определений в режиме статика. Сеть строится в виде треугольников. Все линии (базисы) сети определяются независимо друг от друга, включая линии, опирающиеся на пункты геодезической основы. При этом определяются линии от каждого вновь определяемого пункта не менее, чем до 3 пунктов. Обязательным считается получение замкнутых полигонов. Наблюдения на пунктах опорной геодезической сети выполнить с соблюдением следующих условий:

- дискретность записи измерений - 5 сек;
- маска по возвышению - 15°;
- допустимый коэффициент снижение точности измерения за геометрию пространственной засечки - PDOP < 6 ед.;
- количество одновременно наблюдаемых навигационных спутников не менее 5;
- погрешность центрирования антенны ± 5 мм;
- погрешность измерения высоты антенны ± 3 мм.
- время сеанса наблюдений, зависящее от расстояния между определяемыми пунктами, количества одновременно наблюдаемых навигационных спутников, значений PDOP, - должно быть минимально 1 час.

Обработку данных с GPS-ГЛОНАСС приёмников проводить программой «CREDO GNSS» с выводом ведомостей координат и высот определяемых пунктов и ведомостей точностных показателей результатов обработки.

Другим методом получения координат и высот пунктов геодезической сети является передача данных ГНСС наблюдений для вычисления специалистами ГУП МО «МОБТИ» - СТП МОБТИ по договору с ООО «Инженерные изыскания». Отчет об обработке информации, включающий ведомости обработки RINEX-файлов, схемы получения решения относительно сети базовых станций и относительно пунктов ГГС и список координат вычисленных точек, приводятся в приложении Технического отчета.

Система координат: МСК-50 2 зона

Система высот: Балтийская 1977 г.

Количество пунктов, координаты и высоты которых определяются при помощи спутниковой системы определяются в зависимости от возможностей выбора места ГЛОНАСС-GPS наблюдений и конфигурации съемочной сети. Пункты наблюдения

крепятся временными реперами (деревянный столб, отрезок металлической трубы, уголка и т.д.) или долговременными (грунтовый, стенной, закрепленный на пнях свежесрубленных деревьев, обечайках люков колодцев подземных коммуникаций, оголовках труб и других элементах фундаментальных конструкций), которые обеспечивают их долговременную сохранность и легкий поиск.

Планово-высотное съемочное геодезическое обоснование создается путем проложения образующей полигоны сети теодолитных ходов или линейно-угловой съемочной сети и ходов тригонометрического нивелирования, опирающихся на исходные пункты. Допускается проложение висячих теодолитных ходов, длины (в метрах) которых не должны превышать величин, указанных в табл. 15 ГКИНП-02-033-82. Число сторон в висячих теодолитных ходах на незастроенной территории должно быть не более трех, а на застроенной - не более четырех.

Центрирование тахеометра на станции производится с помощью оптического отвеса с точностью не ниже 2 мм. Измерения на точки хода производится на центр отражателя вехи, сцентрированной по встроенному уровню, двумя полными приемами. Расхождения между значениями одного и того же угла в плане 20″, линии – 0.02 м. Допустимые невязки измерений в линейно-угловых и высотных ходах приняты по табл. 5.1 и 5.2 СП 11-104-97:

- угловые - $1'\sqrt{n}$, где n – число вершин в ходе;
- линейные – 1/2000 – для теодолитных ходов;
- высотные – 50 мм $\sqrt{L}$ (что соответствует техническому нивелированию), где L – длина хода в километрах.

Положение ходов выбирают непосредственно на местности в процессе рекогносцировки. Места для точек хода выбирают так, чтобы обеспечить взаимную видимость между ними, благоприятные условия для съемки окружающей местности, удобства установки геодезических приборов и сохранность точек. Точки съемочной сети закрепляются временными знаками (дюбели, колья).

Линейно-угловая съемочная сеть строится путем измерений со станций на пластиковые ламинированные светоотражающие визирные цели, закрепленные на твердых контурах. Измерения горизонтальных углов выполняются двумя круговыми приемами. При определении высот измерения выполняются методом тригонометрического нивелирования. Каждое превышение определялось двумя полными приемами с изменением местоположения инструмента между ними и изменением положения зрительной трубы (КЛ, КП) внутри приемов. Измерения проводятся в безотражательном режиме. Схема расположения визирных целей и станций наблюдения

выбираются таким образом, чтобы обеспечить с каждой станции наблюдение на как минимум 2 визирные цели, что даст возможность провести совместное уравнивание с оценкой точности положения пунктов.

Привязка к исходным пунктам - координатная (без измерения примычных углов) с выполнением угловых измерений двумя приемами (п. 5.28 СП 11-104-97). Средние погрешности положения пунктов (точек) и средние погрешности определения высот пунктов плановой съемочной геодезической сети приняты по пункту 5.25 СП 11-104-97 (для М 1:500 и сечения рельефа горизонталями через 0.5 м – 0.05 м в плане и по высоте). Вычисление координат и высот съемочного обоснования и оценка точности определения положения пунктов относительно исходных осуществляется в программе «CREDO DAT»

На объекте устанавливаются не менее 2-х знаков долговременного закрепления, которые являются либо исходными пунктами геодезической сети, либо точками хода полигонометрии 2 разряда и нивелирования IV класса, либо определяются засечкой с не менее чем двух точек хода, возможна комбинация из перечисленных вариантов.

В качестве знаков можно использовать: геодезический пункт (грунтовый, стенной, скальный, закрепленный на пнях свежесрубленных деревьев, обечайках смотровых люков колодцев подземных коммуникаций, оголовках труб и других элементах фундаментальных конструкций и т.д.), метод закрепления которого обеспечивает сохранность центра (при условии отсутствия умышленных разрушающих воздействий), а также неизменность его координат и/или отметки в пределах точности геодезической сети, к которой он относится, на период выполнения инженерно-геодезических изысканий и строительства объекта (п. 3.2 СП 47.13330.2016). Знаки долговременного закрепления сдаются на наблюдение за сохранностью представителю Заказчика по акту.

Применяемые инструменты для создания исходной геодезической сети и съемочного обоснования:

– комплект спутникового геодезического приёмника EFT M4 GNSS;
– электронный тахеометр Leika TS02 power;

Выполнение топографической съёмки территории проводится методом горизонтальной и вертикальной съемки электронным тахеометром с точек планово-высотного обоснования или методом линейно-угловой засечки от визирных целей и точек планово-высотного обоснования.

Плановою и высотную привязку съемочных пикетов можно осуществлять с помощью GPS/ГЛОНАСС приемников, работающих в режиме RTK, если позволяет открытость местности. Поправки получают от второго приемника, установленного на пункте планово-высотного обоснования. Можно получать поправки от пунктов сети

постоянно действующих базовых станций (например сети EFT-CORS), в этом случае, для локализации проекции в местной системе координат выполняются измерения на пунктах опорной геодезической сети в режиме RTK с количеством эпох не менее 120 на каждом пункте. Привязку выполнить методом параллельного смещения.

Измерения в режиме RTK выполнить с соблюдением следующих условий:

– количество эпох измерений – 3 и более;

– минимальное количество спутников – 6;

– минимальный угол отсечки наблюдаемых спутников – 10°;

– дискретность записи информации со спутников – 1 секунда;

– максимальный PDOP – 5,0.

– максимальное СКО в плане – 5см

– максимальное СКО в высоте – 5см

Съемке подлежат все объекты и контуры местности, элементы рельефа, предусмотренные действующими Условными знаками для топографической съемки масштаба 1:500 и сечения рельефа горизонталями через 0.5 м. (Инструкция по топографической съемке в масштабах 1:5000, 1:2000, 1:1000 и 1:500 ГКИНП-02-033-82, пп 2.5 и 5). Масштаб 1:500, высота сечения рельефа – 0.5м.

Общая (ориентировочная) площадь топографической съемки – 4.97 га.

Плановая съемка выходов подземных коммуникаций на поверхность выполняется электронным тахеометром со съемочных точек (пунктов ПВО) полярным методом, высотная – методом тригонометрического нивелирования или можно осуществлять с помощью GPS/ГЛОНАСС приемников, работающих в режиме RTK. Для определения коммуникаций, не имеющих выходов на поверхность, используется трубокабелепоисковый комплект "SR - 20". Полнота и правильность нанесения инженерных коммуникаций на топографические планы подтверждаются представителями эксплуатирующих организаций при согласованиях.

Выполнение подеревной съёмки территории производится в процессе топографической съемки. Инвентаризации подлежат деревья с диаметром ствола более 8 см, измеренном на высоте 1.3 м. Каждому дереву и кусту присваивается уникальный номер. Фиксируется: диаметр ствола на высоте 1.3 м., количество стволов из одного комля, порода, характеристика состояния зеленого насаждения. Номера на деревья не наносить.

Общая (ориентировочная) площадь подеревной съемки – 2.5 га.

Камеральная обработка полевых материалов. Вычисления и графические построения чертежей выполнить на ПЭВМ предприятия в программах:

CREDO_GNSS 1.1 - обработка и уравнивание спутниковых определений, составление ведомостей;

CREDO_DAT 4.1 LITE – обработка и уравнивание линейно-угловых измерений, составление ведомостей;

CREDO ТОПОПЛАН 1.11 – построение цифровой модели рельефа;

AutoCAD Civil 3D – построение цифровой модели рельефа, отрисовка ситуации, подготовка листа к печати.

По материалам инженерно-геодезических изысканий, в формате dwg составляется топографический план участка в масштабе 1:500 с сечением рельефа горизонталями через 0.5 м. совмещенный с планом подземных коммуникаций и планом подеревной съемки.

Выпускается перечетная ведомость деревьев и кустарников по форме приложения 5 к Административному регламенту предоставления муниципальной услуги «Выдача разрешения на вырубку, посадку, пересадку зеленых насаждений на территории городского округа Королёв Московской области» в новой редакции», утвержденного Постановлением администрации городского округа Королев от 22.12.2023 №1587-ПА (форма приведена в приложении В программы). По результатам выполнения камеральных работ составляется технический отчет, включающий в себя все графические и текстовые приложения, согласно требований к материалам инженерных изысканий, представляемых по объекту: «МБОУ СОШ на 1100 мест по адресу: Московская область, г. Королев, ул. Гагарина. Кад. ном. участка 50:45:0040322:1152». Виды и объемы запланированных работ сведены в таблицу 1.

Таблица 1

Виды работ	Ед. изм.	Количество
Полевые работы		
Создание планово-высотного геодезического обоснования с использованием GPS (СП 317.1325800.2017 пп. 5.1.3, 5.1.10)	пункт	2 min
Топографическая съемка застроенной территории 2 категории сложности, масштаб 1:500, сечение рельефа 0.5 м. (СП 317.1325800.2017 п. 5.3.2)	га	4.97
Подеревная съемка застроенной территории 2 категории сложности, масштаб 1:500. (СП 317.1325800.2017 п. 5.3.2)	га	2.5
Камеральные работы		
Составление инженерно-топографического плана в масштабе 1:500 с сечением рельефа 0.5 м, совмещенного с планом подземных коммуникаций и планом подеревной съемки. (СП 317.1325800.2017 п. 5.3.3)	га	4.97
Составление перечетной ведомости деревьев и кустарников	шт.	1
Составление программы изысканий (СП 47.13330.2016 п. 5.1.13, 5.1.14)	шт.	1

Составление отчета (СП 47.13330.2016 п.5.1.23)	шт.	1

Применяемые приборы, оборудование, инструменты, программные продукты

- 2 комплекта спутникового геодезического приёмника EFT M4 GNSS – создание планово-высотного обоснования, топографическая съемка, подлежат поверке;
- электронный тахеометр Leika TS02 power - создание планово-высотного обоснования, топографическая съемка, подлежит поверке;
- трубокабелепоисковый комплект "SR - 20" – поиск и определение положения подземных коммуникаций, поверке не подлежит;
- CREDO_GNSS 1.1 - обработка и уравнивание спутниковых определений, составление ведомостей;
- CREDO_DAT 4.1 LITE – обработка и уравнивание линейно-угловых измерений, составление ведомостей;
- CREDO ТОПОПЛАН 1.11 – построение цифровой модели рельефа;
- AutoCAD Civil 3D – построение цифровой модели рельефа, отрисовка ситуации, подготовка листа к печати.
- Для создания текстовых документов использовать: Word, Excel, Adobe Acrobat.

Мероприятия по обеспечению безопасных условий труда при проведении работ

Техника безопасности, охрана труда и окружающей среды при производстве инженерных изысканий организовывается и контролируется руководителем работ в соответствии с нормативно-методическими документами ИОТ 01-23, ИОТ 03-23, ИОТ 05-23, ИОТ 07-23, ИОТ 08-23, ИОТ 24-23. Перед началом работ руководитель обязан проинструктировать работающих об условиях производства работ, проверить состояние инструментов и необходимых приспособлений, правильно расставить рабочих.

Для соблюдения охраны здоровья работающих ежегодно все сотрудники подразделений прошли медицинский осмотр, вакцинацию от клещевого энцефалита, флюорографическое обследование.

Все работающие обеспечены необходимой сезонной спецодеждой, для работы в благоприятный и неблагоприятный периоды.

Все полевые подразделения имеют походные аптечки.

Мероприятия по охране окружающей среды

Предусматривается комплекс мероприятий по охране окружающей среды: недопущение нарушений действующего законодательства по охране окружающей

природной среды, в том числе: несанкционированных вырубок в лесных угодьях, нарушения среды обитания животных и птиц, загрязнения природной среды отходами, нарушения противопожарных норм.

5 Контроль качества и приемка работ

По окончании полевых и камеральных работ начальник партии или главный специалист производит приемочный контроль и оценивает качество выполненных в соответствии с действующими в ООО «Инженерные изыскания» стандартами предприятия с составлением Актов полевой и внутриведомственной приемки инженерно-геодезических работ.

6 Используемые документы и материалы

1 СП 47.13330.2016 - «Инженерные изыскания для строительства. Основные положения. Актуализированная редакция СНиП 11-02-96» с изменениями и дополнениями от 30 декабря 2020 года;

2 СП 11-104-97 - «Инженерно-геодезические изыскания для строительства»;

3 СП 11-104-97 «Инженерно-геодезические изыскания для строительства». Часть II. Выполнение съемки подземных коммуникаций при инженерно-геодезических изысканиях для строительства;

4 СП 126.13330.2017 - «Геодезические работы в строительстве»;

5 СП 317.1325800.2017 - «Инженерно-геодезические изыскания для строительства. Общие правила производства работ»;

6 ГОСТ Р 21.101-2020 «Система проектной документации для строительства (СПДС). Основные требования к проектной и рабочей документации»;

7 ГОСТ 21.301-2021 «Система проектной документации для строительства. Основные требования к оформлению отчетной документации по инженерным изысканиям»;

8 ГКИНП-02-033-82 – «Инструкция по топографической съемке в масштабах 1:5000, 1:2000, 1:1000 и 1:500»;

9 «Правила начертания условных знаков на топографических планах подземных коммуникаций масштабов 1: 1:5000, 1:2000, 1: 1000 и 1:500» - М: «Недра», 1981;

10 «Условные знаки для топографических планов масштабов 1:5000, 1:2000, 1: 1000 и 1:500» - М: ФГУП «Картгеоцентр», 2004г.;

11 ГКИНП (ГНТА)-17-004-99 Инструкция о порядке контроля и приемки геодезических, топографических и картографических работ;

12 ПТБ – 88 Правила по технике безопасности на топографо-геодезических работах.

13 Административный регламент предоставления муниципальной услуги «Выдача разрешения на вырубку, посадку, пересадку зеленых насаждений на территории городского округа Королёв Московской области»

7 Представляемые отчетные материалы

Материалы изысканий выпускаются в виде технического отчета на бумажном носителе, сброшюрованного в тома формата А4 и электронной версии технического отчета, включающей в себя файлы в форматах PDF (заверенные электронной подписью) и DWG.

Материалы изысканий высылаются: Технический отчет

- экз. №№ 2,3 и электронный вид – в адрес заказчика – ООО «Высота» (один экземпляр на бумажном носителе с оригинальными согласованиями);
- экз. №1 отчета хранится в архиве ООО «Инженерные изыскания».

Приложение А
Выписка из реестра членов СРО

НОПРИЗ

АССОЦИАЦИЯ САМОРЕГУЛИРУЕМЫХ ОРГАНИЗАЦИЙ ОБЩЕРОССИЙСКАЯ НЕГОСУДАРСТВЕННАЯ НЕКОММЕРЧЕСКАЯ ОРГАНИЗАЦИЯ – ОБЩЕРОССИЙСКОЕ МЕЖОТРАСЛЕВОЕ ОБЪЕДИНЕНИЕ РАБОТОДАТЕЛЕЙ «НАЦИОНАЛЬНОЕ ОБЪЕДИНЕНИЕ САМОРЕГУЛИРУЕМЫХ ОРГАНИЗАЦИЙ, ОСНОВАННЫХ НА ЧЛЕНСТВЕ ЛИЦ, ВЫПОЛНЯЮЩИХ ИНЖЕНЕРНЫЕ ИЗЫСКАНИЯ, И САМОРЕГУЛИРУЕМЫХ ОРГАНИЗАЦИЙ, ОСНОВАННЫХ НА ЧЛЕНСТВЕ ЛИЦ, ОСУЩЕСТВЛЯЮЩИХ ПОДГОТОВКУ ПРОЕКТНОЙ ДОКУМЕНТАЦИИ»

5050093095-20250407-1122 (регистрационный номер выписки)

07.04.2025 (дата формирования выписки)

ВЫПИСКА
из единого реестра сведений о членах саморегулируемых организаций в области инженерных изысканий и в области архитектурно-строительного проектирования и их обязательствах

Настоящая выписка содержит сведения о юридическом лице (индивидуальном предпринимателе), выполняющем инженерные изыскания:

Общество с ограниченной ответственностью "Инженерные изыскания"
(полное наименование юридического лица/ФИО индивидуального предпринимателя)

1115050007775
(основной государственный регистрационный номер)

1. Сведения о члене саморегулируемой организации:		
1.1	Идентификационный номер налогоплательщика	5050093095
1.2	Полное наименование юридического лица (Фамилия Имя Отчество индивидуального предпринимателя)	Общество с ограниченной ответственностью "Инженерные изыскания"
1.3	Сокращенное наименование юридического лица	ООО "Инженерные изыскания"
1.4	Адрес юридического лица Место фактического осуществления деятельности (для индивидуального предпринимателя)	141107, Россия, Московская область, г.Щелково, ул. Браварская, д.2, В, строение 1, пом.25
1.5	Является членом саморегулируемой организации	Саморегулируемая ассоциация «Объединение инженеров-изыскателей в строительстве» (СРО-И-027-03032010)
1.6	Регистрационный номер члена саморегулируемой организации	И-027-005050093095-0081
1.7	Дата вступления в силу решения о приеме в члены саморегулируемой организации	15.12.2011
1.8	Дата и номер решения об исключении из членов саморегулируемой организации, основания исключения	

2. Сведения о наличии у члена саморегулируемой организации права выполнять инженерные изыскания:		
2.1 в отношении объектов капитального строительства (кроме особо опасных, технически сложных и уникальных объектов, объектов использования атомной энергии) (дата возникновения/изменения права)	2.2 в отношении особо опасных, технически сложных и уникальных объектов капитального строительства (кроме объектов использования атомной энергии) (дата возникновения/изменения права)	2.3 в отношении объектов использования атомной энергии (дата возникновения/изменения права)
Да, 15.12.2011	Да, 15.12.2011	Нет

1

3. Компенсационный фонд возмещения вреда		
3.1	Уровень ответственности члена саморегулируемой организации по обязательствам по договору подряда на выполнение инженерных изысканий, в соответствии с которым указанным членом внесен взнос в компенсационный фонд возмещения вреда	**Первый уровень ответственности (не превышает двадцать пять миллионов рублей)**
3.2	Сведения о приостановлении права выполнять инженерные изыскания объектов капитального строительства	
4. Компенсационный фонд обеспечения договорных обязательств		
4.1	Дата, с которой член саморегулируемой организации имеет право выполнять инженерные изыскания по договорам подряда, заключаемым с использованием конкурентных способов заключения договоров, в соответствии с которым указанным членом внесен взнос в компенсационный фонд обеспечения договорных обязательств	**01.07.2017**
4.2	Уровень ответственности члена саморегулируемой организации по обязательствам по договорам подряда на выполнение инженерных изысканий, заключаемым с использованием конкурентных способов заключения договоров, в соответствии с которым указанным членом внесен взнос в компенсационный фонд обеспечения договорных обязательств	**Второй уровень ответственности (не превышает пятьдесят миллионов рублей)**
4.3	Дата уплаты дополнительного взноса	**Нет**
4.4	Сведения о приостановлении права выполнять инженерные изыскания по договорам подряда, заключаемым с использованием конкурентных способов заключения договоров	
5. Фактический совокупный размер обязательств		
5.1	Фактический совокупный размер обязательств по договорам подряда на выполнение инженерных изысканий, заключаемым с использованием конкурентных способов заключения договоров на дату выдачи выписки	**Нет**

Руководитель аппарата

НОПРИЗ

ДОКУМЕНТ ПОДПИСАН УСИЛЕННОЙ КВАЛИФИЦИРОВАННОЙ ЭЛЕКТРОННОЙ ПОДПИСЬЮ

Владелец: Кожуховский Алексей Олегович

123056, г. Москва, ул. 2-ая Брестская, д.5

СЕРТИФИКАТ 053be38e002cb2f5ae4596563321274ad8

ДЕЙСТВИТЕЛЕН: С 18.11.2024 ПО 18.11.2025

А.О. Кожуховский

2

Приложение Б
Техническое задание

Согласовано:
Генеральный директор
ООО «Высота»

_____ **И.Н. Гарин**
22 апреля 2025 г.

Утверждаю:
Первый зам. генерального директора
ГКУ МО «ДЗКС»

_____ **А.А. Барсков**
22 апреля 2025 г.

Согласовано:
Генеральный директор
ООО «Инженерные изыскания»

_____ **А.В. Шульго**
22 апреля 2025 г.

ТЕХНИЧЕСКОЕ ЗАДАНИЕ
на выполнение инженерно-геодезических изысканий по объекту:

1	Наименование объекта:	МБОУ СОШ на 1100 мест по адресу: Московская область, г. Королев, ул. Гагарина. Кад. ном. участка 50:45:0040322:1152
2	Местоположение объекта	Московская область, г. Королев, в 33 метрах по направлению на юг от д. 12/14 по ул. Гагарина
3	Основание для выполнения работ	Договор №104 от 22 апреля 2025г.
4	Вид градостроительной деятельности	Новое строительство
5	Идентификационные сведения о Заказчике	ООО «ВЫСОТА» Генеральный директор ООО Высота» И.Н. Гарин. Юридический адрес: 143968, Московская область, г.о. Реутов, г. Реутов, проезд Северный, д. 7 ИНН 5012034645; КПП 504101001
6	Идентификационные сведения об исполнителе	ООО «Инженерные изыскания». Генеральный директор – Шульго А.В. Юридический адрес: 141107, Московская обл., г. Щелково, ул. Браварская, д. 2В, строение 1, помещение 25, in.iz56@yandex.ru. ИНН 5050093095; КПП 505001001
7	Ответственный представитель заказчика	Гарин Иван Николаевич 8-977-457-70-97, smrzakaz@gmail.com
8	Вид инженерных изысканий	Инженерно- геодезические изыскания для архитектурно-строительного проектирования при подготовке проектной

		документации объектов капитального строительства. Первый этап.
9	Цели и задачи инженерно-геодезических изысканий	Цель инженерно-геодезических изысканий – получение исходных топографо-геодезических данных: инженерно-топографических планов в графическом и/или цифровом видах представления информации; сведений о координатах и отметках точек местности; количественных характеристик развития опасных природных и техногенных процессов; иных материалов и данных, необходимых для разработки генерального плана проектируемого объекта капитального строительства и обеспечения выполнения других видов инженерных изысканий
10	Данные о местоположении и границах площадки	Земельный участок 50:45:0040322:1152, Категория земель: Земли населённых пунктов, Разрешенное использование: для строительства общеобразовательной школы на 1100 мест. Границы участка топографической съемки согласно схемы, приложение 1, ориентировочная площадь – 4.97 га.
11	Принадлежность к объектам транспортной инфраструктуры и к другим объектам, функционально-технологические особенности которых влияют на их безопасность	Не принадлежит
12	Возможность опасных природных процессов и явлений и техногенных воздействий на территории, на которой будут осуществляться строительство, реконструкция и эксплуатация здания или сооружения	Не прогнозируется
13	Принадлежность к опасным производственным объектам	Не принадлежит
14	Класс функциональной пожарной опасности	Ф4.1 (Федеральный закон от 22 июля 2008 г. N 123-ФЗ «Технический регламент о требованиях пожарной безопасности»)
15	Класс конструктивной пожарной опасности	С0 Степень огнестойкости II
16	Класс возможного пожара на объекте	Определить по результатам инженерных изысканий (комплексноо инженерно-технического обследования состояния объекта), в соответствии с требованиями Федерального закона от 22.07.2028 № 123-ФЗ «Технический регламент о требованиях пожарной безопасности»
17	Характеристики проектируемых задний и сооружений	Общая площадь: 3904.1 $м^2$; площадь ЗУ 2262 $м^2$; площадь застройки 1646.1 $м^2$; строительный объем 19164 $м^3$
18	Технические требования к производству работ	Масштаб: 1:500; Высота сечения рельефа: 0,5 метра; Система координат – МСК-50; Система высот – Балтийская 1977 г. Выполнить подеревную съемку в границах кадастрового участка 50:45:0040322:1152. Ориентировочная площадь подеревной съемки – 2.5 га Инвентаризации подлежат деревья с диаметром ствола более 0.1 м, измеренном на высоте 1.3 м. Каждому дереву присваивается

		уникальный номер, фиксируется: диаметр ствола на высоте 1.3 м., порода, характеристика состояния. Номера на деревья не наносить. Выпустить перечетную ведомость деревьев.
19	Перечень нормативных документов	1. СП 47.13330.2016 Инженерные изыскания для строительства. Основные положения. С изменениями и дополнениями от 30.12.2020 г; 2. СП 317.1325800.2017. Свод правил. Инженерно-геодезические изыскания для строительства. Общие правила производства работ" (утв. и введен в действие Приказом Минстроя России от 22.12.2017 N 1702/пр.); 3. СП 11-104-97 Инженерно-геодезические изыскания для строительства; 4. - СП 11-104-97 «Инженерно-геодезические изыскания для строительства». Часть II. Выполнение съемки подземных коммуникаций при инженерно-геодезических изысканиях для строительства; 5. ГКИНП-02-033-82; Инструкция по топографической съемке в масштабах 1:5000-1:500; 6. Условные знаки для топографических планов масштабов 1:5000-1:500.
20	Требования к составу, срокам, порядку, и форме представления изыскательской продукции заказчику	1. Технический отчет на бумажном носителе, сброшюрованный в том формата А4 - 2 экз., в электронном виде на CD-диске – 1 экз. 2. Инженерно-топографический план участка М 1:500 в электронном виде в формате AutoCAD (*.dwg) 3. Срок предоставления: согласно договору

Приложение 1

Схема границ топографической съемки

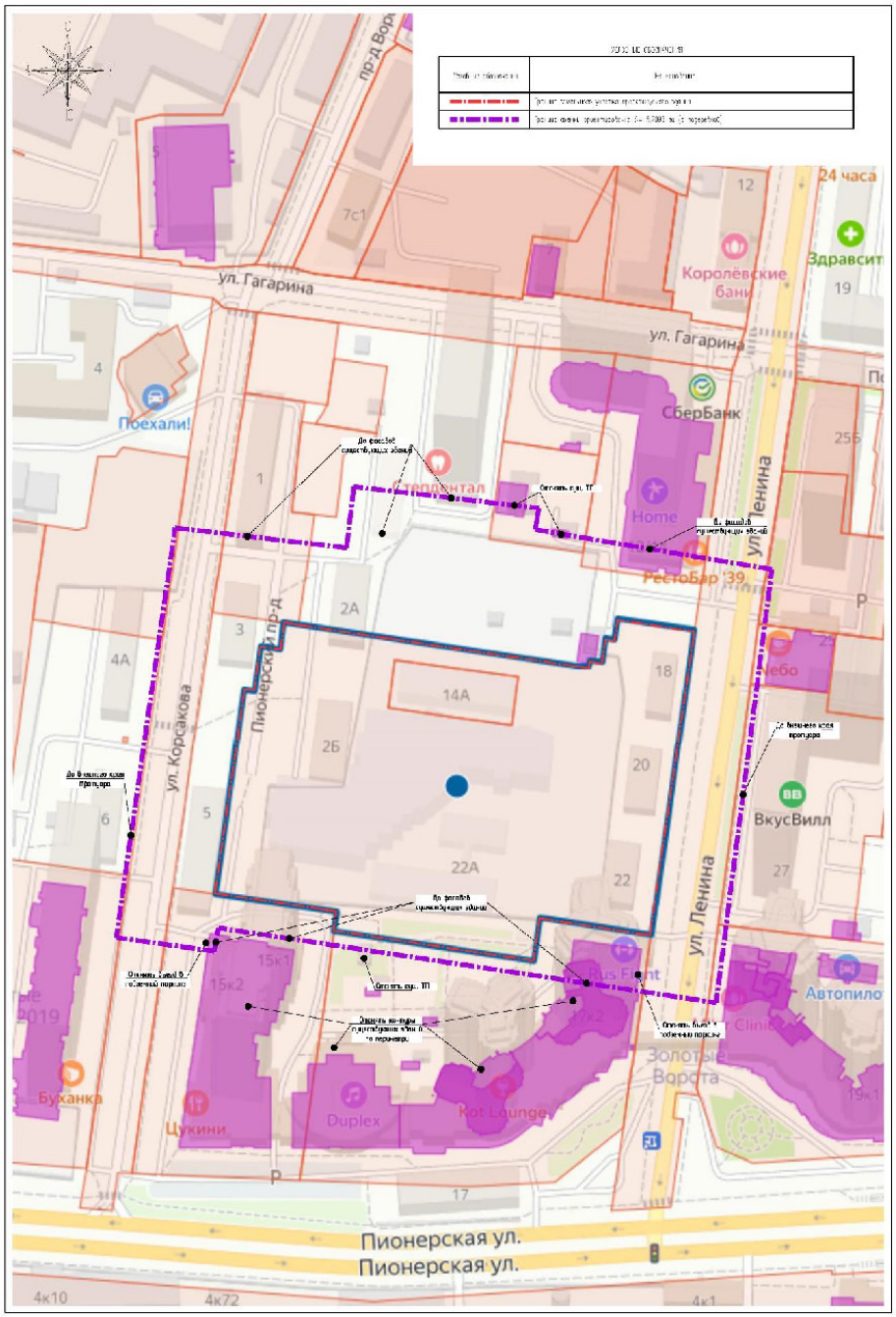

Взам. инв. №	
Подп. и дата	
Инв. № подл.	

Изм.	Кол.у	Лист	№док	Подп.	Дата	819-ИГДИ-П-Т	Лист 21

Формат

Приложение В
Выписка из Административного регламента

Приложение 5
к Административному регламенту предоставления муниципальной услуги "Выдача разрешения на вырубку, посадку, пересадку зеленых насаждений на территории городского округа Королев Московской области", одобренной на заседании Комиссии по проведению административной реформы в Московской области от 19.04.2023 N 5

Перечетная ведомость деревьев и кустарников

Перечетная ведомость деревьев и кустарников, расположенных по адресу: _____
_____,
(указывается адрес (месторасположение) зеленых насаждений, кадастровый номер земельного участка)

№ п/п	Наименование породы	Количество, ед.		Диаметр, см	Характеристика состояния зеленых насаждений	Примечание
		деревьев	кустарников			
1	2	3	4	5	6	7
	Итого:					

Количество деревьев и кустарников:
подлежащих вырубке деревьев _____ ед., кустарников _____ед.,
подлежащих пересадке деревьев _____ ед., кустарников _____ ед.,
подлежащих посадке деревьев _____ед., кустарников _____ ед.,

Площадь уничтожаемого травяного покрова (газона) _____ кв.м

Составлена
_____.
(полное наименование организации, фамилия, имя, отчество (при наличии) - для физического лица, индивидуального предпринимателя или полное наименование юридического лица)

_____
Заявитель (представитель заявителя) подпись (расшифровка подписи)

Дата "___" _____ 20___

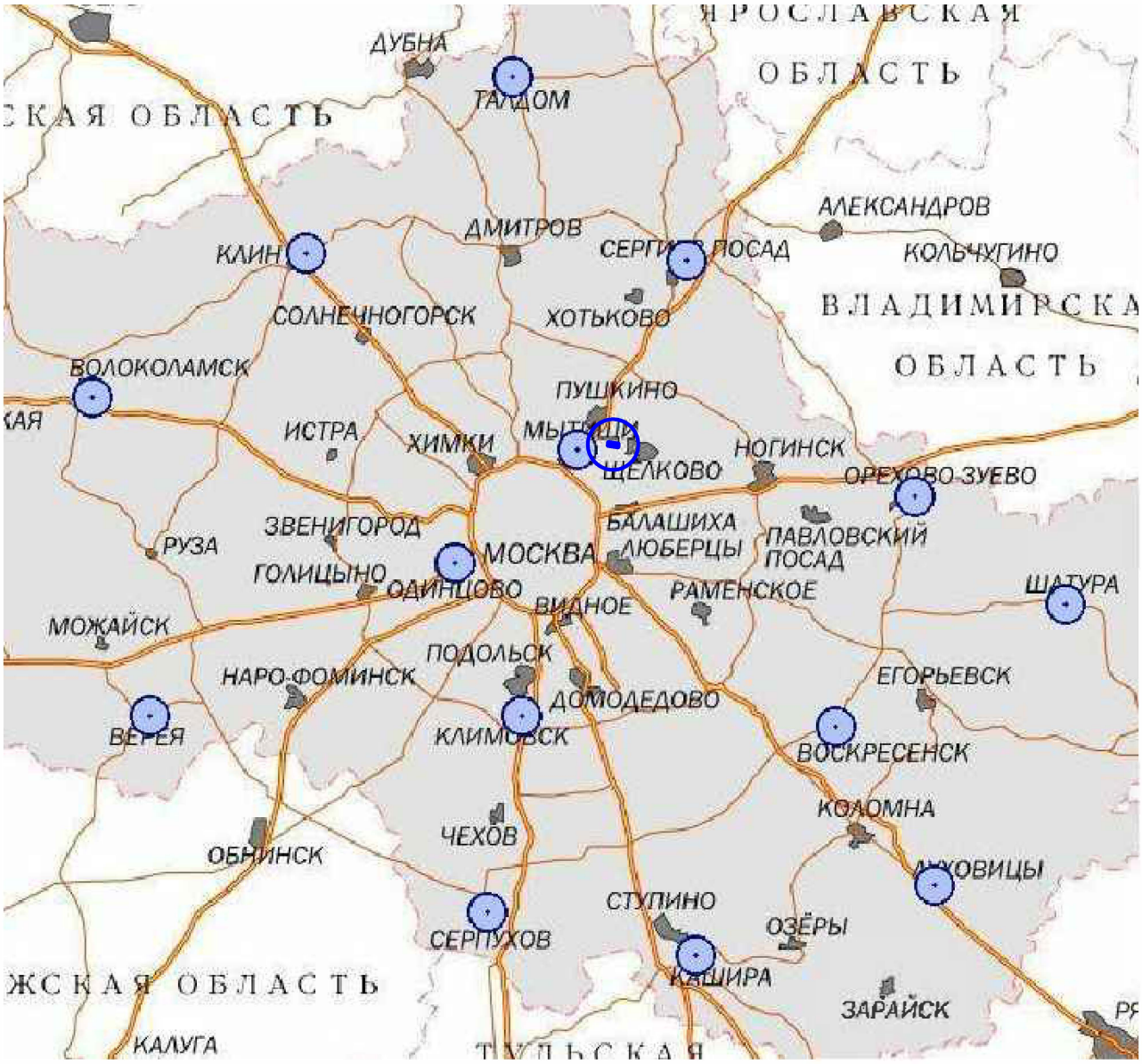

Условные обозначения

– базовые станции СТП МОБТИ

– место расположения участка топосъемки

Согласовано

Взамен инв. N

Подпись и дата

Инв. N подл.

Изм.	Кол.уч.	Лист	№ док	Подпись	Дата
Разработал		В.Ковов			06.05.2025
Проверил		И.Шахова			06.05.2025
Н. контр.		Л.Бешар			06.05.2025
Нач. отдела		М.Семенов			06.05.2025

819–ИГДИ–П–Г.1

МБОУ СОШ на 1100 мест: Московская область, г. о. Королев, ЖК "Золотые ворота"

Инженерно–геодезические изыскания

стадия	лист	листов
И	1	1

Картограмма топографо–геодезической изученности

ООО "Инженерные изыскания" г. Щелково

Формат А4