ИП РЫБКИН ВЛАДИМИР ИЛЬИЧ
ОГРН 323774600408320
ИНН 732302533984
Тел./факс:+7(926)658-67-73
e-mail: rybkinvladimir@yandex.ru

Саморегулируемая организация Союз проектных организаций "ПроЭк" (СРО-П-185-16052013)
П-185-732302533984-2637 от 24.04.2024

Заказчик:
Администрация городского округа Зарайск Московской области

Многоквартирный жилой дом по адресу: Московская область, городской округ Зарайск, ул. Московская

ПРОЕКТНАЯ ДОКУМЕНТАЦИЯ

Раздел 11
Мероприятия по обеспечению доступа инвалидов к объекту капитального строительства

МКД-0109-2024-ПИР-ОДИ

Том 11

Индивидуальный предприниматель **В.И. Рыбкин**

Главный инженер проекта **В.И. Рыбкин**

2025

Содержание раздела

Лист	Наименование	Примечания
1.1	Титульный лист	
1.2	Содержание раздела	
1.3	Заверение проектной организации о соответствии проектных решений требованиям нормативных документов	
	Текстовая часть	
1.4	1. Перечень мероприятий по обеспечению доступа инвалидов к объектам, предусмотренным в пункте 10 части 12 статьи 48 Градостроительного кодекса Российской Федерации	
1.4	2. Обоснование принятых конструктивных, объемно-планировочных и иных технических решений, обеспечивающих безопасное перемещение инвалидов по объекту, а также их эвакуацию из объекта в случае пожара или стихийного бедствия	
	Графическая часть	
2	Схема планировочной организации участка с указанием путей перемещения инвалидов	
3	Схема путей перемещения и эвакуации инвалидов по 1 этажу. Секция 1	
4	Схема путей перемещения и эвакуации инвалидов по 1 этажу. Секция 2	
5	Схема путей перемещения и эвакуации инвалидов по 1 этажу. Секция 3	

Взам. инв. №

Подпись и дата

Инв. № подл.

Изм.	Кол.уч.	Лист	№док.	Подпись	Дата
ГИП		Рыбкин			07.25
Разработал		Винокуров			07.25
Проверил		Степанов			07.25

МКД-0109-2024-ПИР-ОДИ

Мероприятия по обеспечению доступа инвалидов. Пояснительная записка

Стадия	Лист	Листов
П	1.2	6

ИП РЫБКИН ВЛАДИМИР ИЛЬИЧ

Заверение проектной организации о соответствии проектных решений требованиям нормативных документов

Проектная документация разработана в соответствии с градостроительным планом земельного участка, заданием на проектирование, градостроительным регламентом, документами об использовании земельного участка для строительства, техническими регламентами, в том числе устанавливающими требованиям по обеспечению безопасной эксплуатации зданий, строений, сооружений и безопасного использования прилегающих к ним территорий с соблюдением технических условий.

ГИП *Рыбкин В. И.*

1. Перечень мероприятий по обеспечению доступа инвалидов к объектам, предусмотренным в пункте 10 части 12 статьи 48 Градостроительного кодекса Российской Федерации

Заданием на проектирование доступ МГН на 1 этаж, квартиры для МГН отсутствуют.

При входных группах секций предусмотрена возможность доступа для маломобильных групп населения.

В проекте предусмотрены следующие мероприятия по обеспечению доступности здания и прилегающей территории для маломобильных групп населения:

- тротуары и пешеходные дорожки на путях движения инвалидов в местах сопряжения с проездами оборудованы пандусами с продольным уклоном не более 6%, поперечным уклоном не более 1% и шириной не менее 1,5 метра для создания доступной (безбарьерной) среды;
- ширина путей движения на участке для инвалидов на креслах-колясках составляет не менее 2,0 метров согласно СП 59.13330.2020;
- система средств информационной поддержки обеспечена на всех путях движения, доступных для МГН в течение всего времени их пребывания в здании;
- над входными площадками предусмотрены козырьки, предохраняющие их от атмосферных осадков, оборудованные системой организованного водоотведения.

Проектные решения, предназначенные для маломобильных групп населения, не ограничивают условия жизнедеятельности и не ущемляют права и возможности других групп населения, находящихся в здании.

2. Обоснование принятых конструктивных, объемно-планировочных и иных технических решений, обеспечивающих безопасное перемещение инвалидов по объекту, а также их эвакуацию из объекта в случае пожара или стихийного бедствия

Основное внимание при выполнении указанных в вышележащем пункте мероприятий направлено на обеспечение беспрепятственного передвижения по территории, а также в самом здании маломобильных групп населения, как пешком (в том числе с помощью трости и костылей), так и с помощью кресла-коляски. При этом доступ для МГН обеспечен – на 1 этаж. Подвал не предназначен для посещения инвалидами.

Движение по территории граждан, относящихся к категории МГН, обеспечивается по тротуарам шириной не менее 2 метров. В местах сопряжения с проездами тротуары оборудованы пандусами с продольным уклоном не более 6%, поперечным уклоном не более 1% и шириной не менее 1,5 метра. В местах пересечения путей для движения МГН с транспортными путями высота бортовых камней тротуара не превышает 1,5 см. Высота бордюров по краям пешеходных тротуаров не превышает 5 см.

Для покрытия пешеходных дорожек, тротуаров и пандусов, которыми могут пользоваться граждане, относящиеся к категории МГН, применяется тротуарная плитка с шероховатой поверхностью.

Поверхности покрытий входных площадок и тамбуров твёрдые, не допускающие скольжения при намокании и имеют поперечный уклон в пределах 1%. Поверхности покрытий полов в здании, по которым осуществляется передвижение инвалидов, имеют твердую и прочную нескользкую поверхность.

Пути движения МГН по надземным этажам здания соответствуют нормативным требованиями к путям эвакуации.

Ширина проемов на путях возможного передвижения инвалидов в свету не менее 1,0м (в чистоте). Высота проходов до низа выступающих конструкций не менее 2,1м; до низа ветвей деревьев – не менее 2,2м.

Наружные входные двери оборудованы фиксаторами в положении «закрыто» / «открыто» и обозначены средствами визуальной коммуникации, с яркой контрастной маркировкой на уровне 1,5м от поверхности крыльца. Все двери на пути движения МГН оборудованы ручками, позволяющие инвалиду управлять ими одной рукой, не прилагая значительных усилий.

Во составе всех входных зон всех секций предусмотрены подъемники для МГН.

На 1 этаже в каждой секции в лестничных клетках предусмотрены пожаробезопасные зоны МГН.

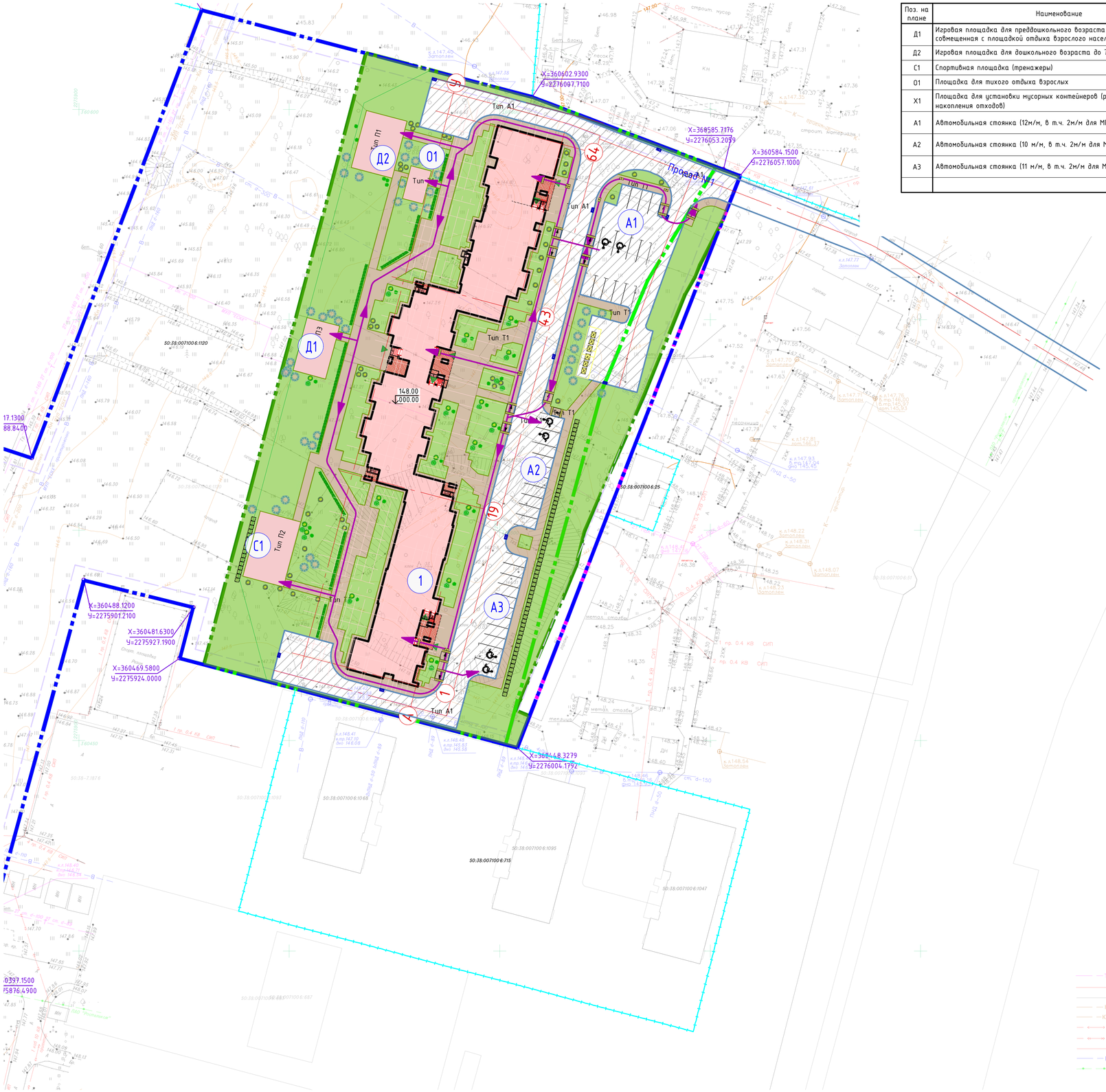

Ведомость площадок

Поз. на плане	Наименование	Примечание
Д1	Игровая площадка для преддошкольного возраста до 3-х лет совмещенная с площадкой отдыха взрослого населения	104,0 м²
Д2	Игровая площадка для дошкольного возраста до 7 лет	140.0 м²
С1	Спортивная площадка (тренажеры)	160,0 м²
О1	Площадка для тихого отдыха взрослых	40,0 м²
Х1	Площадка для установки мусорных контейнеров (раздельного накопления отходов)	20,0 м²
А1	Автомобильная стоянка (12м/м, в т.ч. 2м/м для МГН)	
А2	Автомобильная стоянка (10 м/м, в т.ч. 2м/м для МГН)	
А3	Автомобильная стоянка (11 м/м, в т.ч. 2м/м для МГН)	

Экспликация зданий и сооружений

№ на плане	Наименование	Примечание
1	Жилой многоквартирный дом (4 этажа)	проектируемый

Основные показатели генплана

Поз.	Наименование показателя	Ед.изм.	Количество	Примечание
1	Площадь земельного участка в границах благоустройства	м²	12038,3	
3	Площадь застройки	м²	1970,3	
4	Площадь твёрдых покрытий, в т.ч.:	м²	5547,5	
	под нависающими частями здания	м²	120,2	
5	Площадь озеленения (в плане)	м²	4639,7	

Условные обозначения

- Граница участка по ГПЗУ
- Граница благоустройства
- Здания и сооружения перспектива
- Здания и сооружения по отдельному проекту
- Проектируемые здания и сооружения
- Проектируемые консольно выступающие части здания или части здания на опорах
- Проектируемый бортовой камень БР100.30.15
- Бортовой камень БР100.20.08
- Металлический бордюр 1200*120*70*1,5
- Пониженный бортовой камень
- Граница площадки, полосы движения
- Откос
- Дождеприемная решетка
- Контейнеры ТБО с навесом
- Машино-места для МГН
- Машино-места
- Опора освещения
- Проектируемые проезды из асфальтобетона Тип А1
- Проектируемые тротуары и площадки с возможностью проезда пожарной техники из бетонной плитки Тип Т1
- Детские площадки Тип П1
- Проектируемое озеленение (газон)
- Кустарники высотой до 2,5м
- Кустарники высотой 0,5-0,7 м
- Кустарники высотой до 1,1м (живая изгородь)
- Кустарник высотой до 0,7м (бордюр)
- Маркер озеленения (1/5)
- пути перемещения инвалидов

Условные обозначения:

- теплотраса подземная
- электрокабель ВВ надземный
- граница кадастрового участка
- канализация
- канализация напорная
- электрокабель НВ подземный
- электрокабель ВВ подземный
- электрокабель НВ надземный
- водопровод подземный
- кабель связи подземный

Ведомость тактильной плитки

Обозначение	Условное обозначение	Наименование	Размер	Кол-во
Тактильная плитка - диагональный риф		Плитка бетонная	500x500мм	8шт.
Тактильная плитка - продольный риф		Плитка бетонная	500x500мм	112шт.

Изм.	Кол.уч.	Лист	№док.	Подпись	Дата	МКД-0109-2024-ПИР-ОДИ			
						Многоквартирный жилой дом по адресу: "Московская область, городской округ Зарайск, ул. Московская"			
Разработал		Ларкина			28.08.25	Многоквартирный жилой дом	Стадия	Лист	Листов
Проверил		Степанов			28.08.25			2	
Н.контроль		Макарова			28.08.25	Схема планировочной организации участка с указанием путей перемещения инвалидов	ИП РЫБКИН ВЛАДИМИР ИЛЬИЧ		
ГИП		Рыбкин			28.08.25				

Согласовано:

Взам. инв. №

Подпись и дата

Инв. № подл.

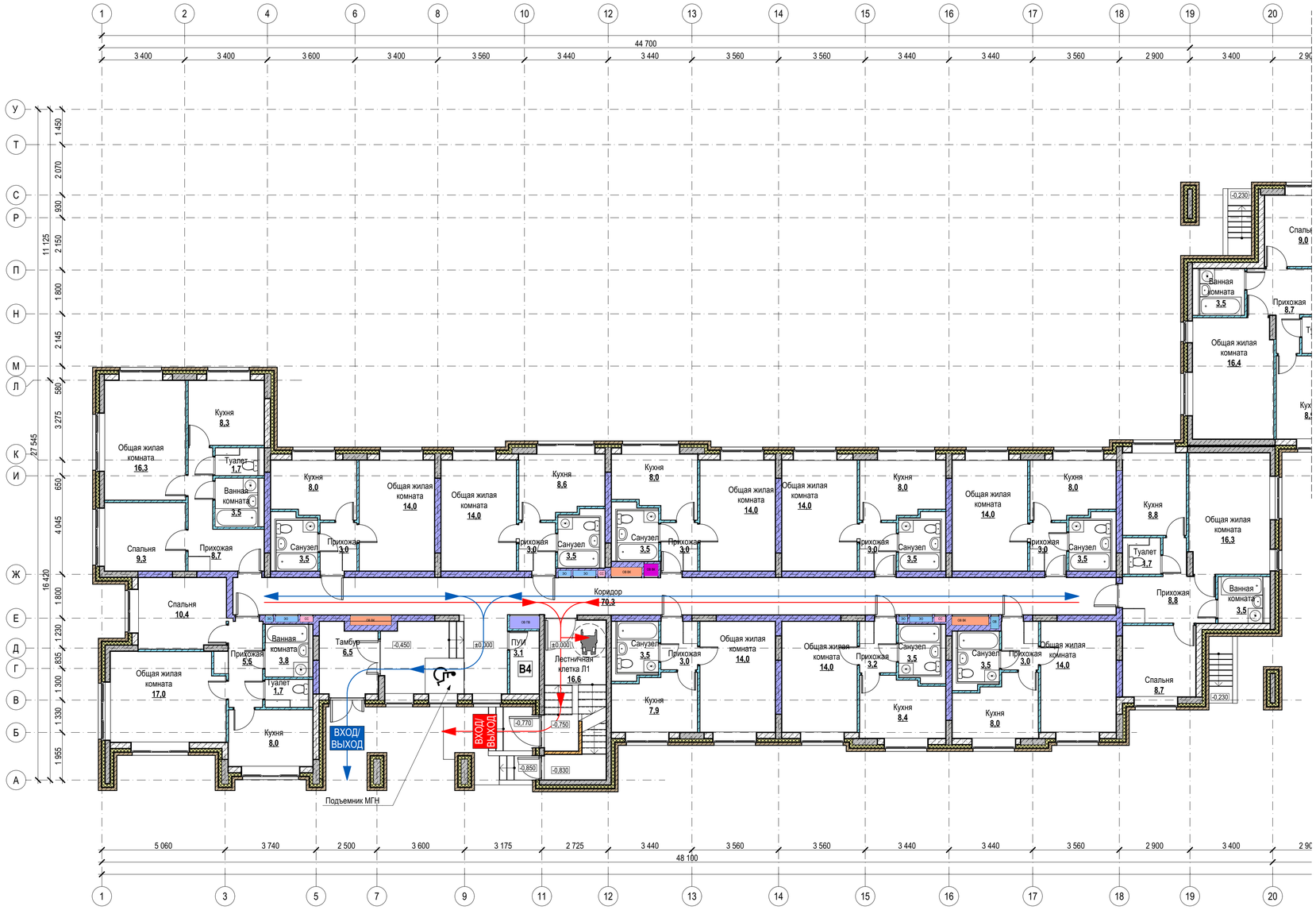

Условные обозначения

- Пути движения МГН
- Пути эвакуации МГН
- ВХОД/ВЫХОД — Вход/выход на этаж

Компоновочная схема

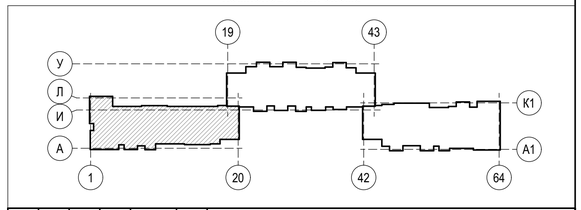

						МКД-0109-2024-ПИР-ОДИ			
						Многоквартирный жилой дом по адресу: "Московская область, городской округ Зарайск, ул. Московская"			
Изм.	Кол.уч.	Лист	№док.	Подпись	Дата				
Разработал		Ларкина			28.08.25	Многоквартирный жилой дом	Стадия	Лист	Листов
Проверил		Степанов			28.08.25		П	3	
Н.контроль		Макарова			28.08.25	Схема перемещения и эвакуации инвалидов по 1 этажу. Секция 1	ИП РЫБКИН ВЛАДИМИР ИЛЬИЧ		
ГИП		Рыбкин			28.08.25				

Согласовано:

Взам. инв. №

Подпись и дата

Инв. № подл.

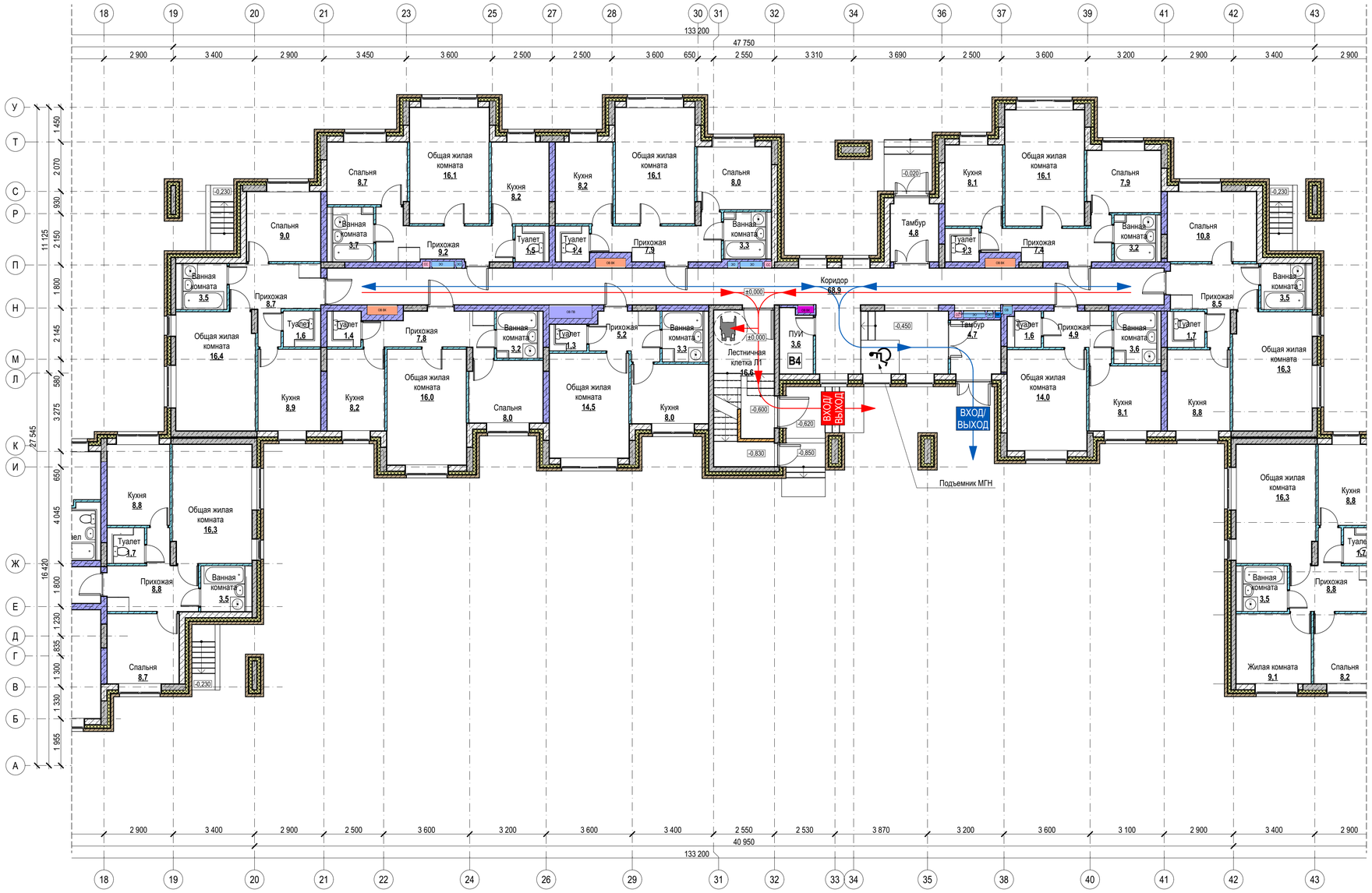

Условные обозначения

- Пути движения МГН
- Пути эвакуации МГН
- ВХОД/ВЫХОД — Вход/выход на этаж

Компоновочная схема

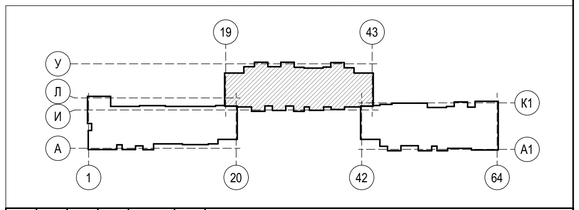

Изм.	Кол.уч.	Лист	№док.	Подпись	Дата	МКД-0109-2024-ПИР-ОДИ
						Многоквартирный жилой дом по адресу: "Московская область, городской округ Зарайск, ул. Московская"
Разработал		Ларкина			28.08.25	Многоквартирный жилой дом — Стадия: П; Лист: 4; Листов:
Проверил		Степанов			28.08.25	
Н.контроль		Макарова			28.08.25	Схема перемещения и эвакуации инвалидов по 1 этажу. Секция 2
ГИП		Рыбкин			28.08.25	ИП РЫБКИН ВЛАДИМИР ИЛЬИЧ

Согласовано:

Взам. инв. №

Подпись и дата

Инв. № подл.

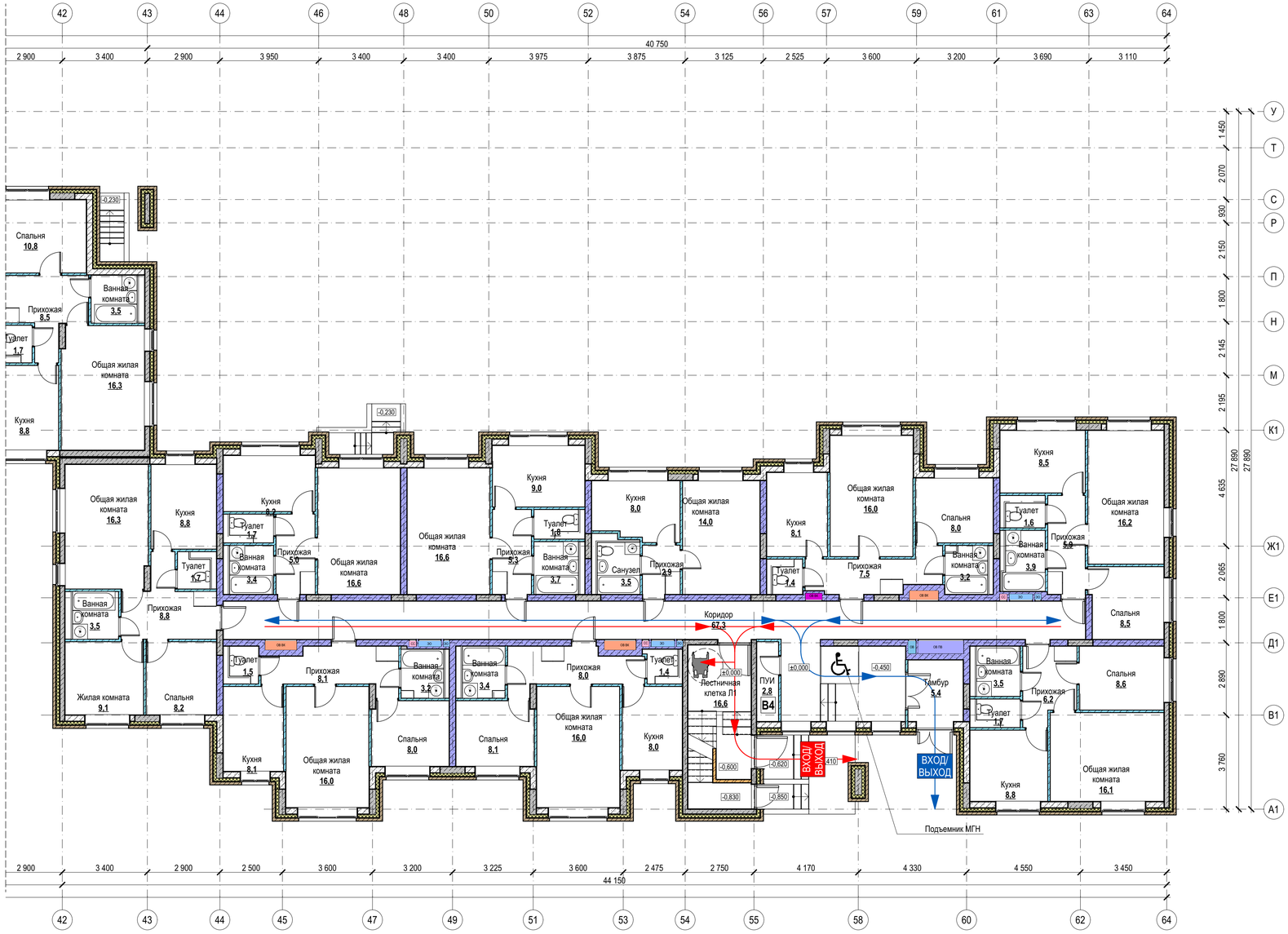

Условные обозначения

- Пути движения МГН
- Пути эвакуации МГН
- ВХОД/ВЫХОД — Вход/выход на этаж

Компоновочная схема

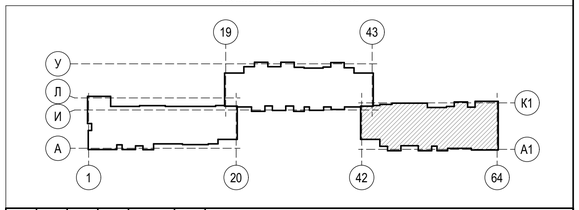

Изм.	Кол.уч.	Лист	№док.	Подпись	Дата	МКД-0109-2024-ПИР-ОДИ
						Многоквартирный жилой дом по адресу: "Московская область, городской округ Зарайск, ул. Московская"
Разработал		Ларкина			28.08.25	Многоквартирный жилой дом — Стадия: П; Лист: 5; Листов:
Проверил		Степанов			28.08.25	
Н.контроль		Макарова			28.08.25	Схема перемещения и эвакуации инвалидов по 1 этажу. Секция 3
ГИП		Рыбкин			28.08.25	ИП РЫБКИН ВЛАДИМИР ИЛЬИЧ

Согласовано:

Взам. инв. №

Подпись и дата

Инв. № подл.